

**BOLLETTINO DI VIGILANZA METEOROLOGICA NAZIONALE**

**RIFE// DIRETTIVA PRESIDENTE DEL CONSIGLIO DEI MINISTRI 27-2-2004:**

**INDIRIZZI OPERATIVI PER LA GESTIONE ORGANIZZATIVA E FUNZIONALE DEL SISTEMA DI ALLERTAMENTO NAZIONALE, STATALE E REGIONALE, PER IL RISCHIO IDROGEOLOGICO E IDRAULICO AI FINI DI PROTEZIONE CIVILE**

**FENOMENI SIGNIFICATIVI O AVVERSI PER IL GIORNO 23 GENNAIO 2026**

**Precipitazioni:**

- sparse, localmente anche a carattere di rovescio o temporale, su Liguria di Levante, Toscana settentrionale e tirrenica e coste occidentali della Sardegna, con quantitativi cumulati da deboli a puntualmente moderati;
- da isolate a sparse sui restanti settori di Liguria, Toscana e Sardegna e su Piemonte, Valle d'Aosta, Lombardia, Trentino, Veneto centro-meridionale, Emilia-Romagna, Umbria centro-settentrionale e occidentale, Marche centro-settentrionali, Lazio e settore tirrenico della Campania settentrionale, con quantitativi cumulati deboli.

Nevicata: a quote superiori a 100-300 m su Piemonte sud-orientale, entroterra della Liguria centrale e Lombardia sud-occidentale, con apporti al suolo deboli; al di sopra dei 300-500 m su Piemonte sud-occidentale, entroterra della Liguria di Ponente e settore più occidentale dell'Appennino emiliano, con apporti al suolo deboli; al di sopra dei 600-900 m sul resto del Piemonte e sulla Valle d'Aosta, con apporti al suolo deboli; al di sopra degli 800-1000 m sui settori alpini e prealpini della Lombardia e sulle Prealpi del Veneto, con apporti al suolo deboli; al di sopra dei 1200-1400 m sul resto dell'Appennino emiliano-romagnolo e su quello ligure e toscano, con apporti al suolo da deboli a moderati; possibili episodi di pioggia congelantesi nei fondovalle dell'Appennino settentrionale, ligure ed emiliano.

**Visibilità:** nessun fenomeno significativo.

**Temperature:** nessun fenomeno significativo.

**Venti:** localmente forti sud-occidentali sulla Sardegna meridionale; tendenti a forti sud-occidentali sui crinali dell'Appennino tosco-romagnolo e umbro-marchigiano.

**Mari:** da molto mosso ad agitato il Canale di Sardegna; molto mossi il Mar di Sardegna, lo Stretto di Sicilia, lo Ionio meridionale, tendenti a molto mossi il Tirreno meridionale e il Mar Ligure.

**FENOMENI SIGNIFICATIVI O AVVERSI PER IL GIORNO 24 GENNAIO 2026**

**Precipitazioni:**

- da sparse a diffuse, anche a carattere di rovescio o temporale, su Liguria di Levante, Toscana settentrionale, crinali dell'Appennino emiliano, Lazio, settori occidentali di Abruzzo e Molise, versanti occidentali e zone interne settentrionali della Campania, e sui settori occidentali della Sardegna, con quantitativi cumulati moderati sui settori centro-meridionali e zone interne settentrionali del Lazio e sulla Campania centro-settentrionale, da deboli a puntualmente moderati sulle restanti zone;
- sparse sul resto del Centro-Nord e della Campania e su Puglia, Basilicata, settore tirrenico della

Calabria settentrionale e sulla Sicilia centro-occidentale, con quantitativi cumulati generalmente deboli.

**Nevicate:** al di sopra dei 200-400 m sul Piemonte meridionale e sull'entroterra della Liguria centrale, con apporti al suolo moderati; al di sopra dei 500-700 m sul resto del Piemonte, sulla Valle d'Aosta, sulla Lombardia nord-occidentale, sull'entroterra della Liguria di Ponente e sull'Appennino emiliano, con apporti al suolo da deboli a moderati; al di sopra dei 800-1100 m sul resto dei settori alpini e prealpini lombardi e su quelli del Triveneto, con apporti al suolo da deboli a moderati; al di sopra dei 1200-1400 m sull'Appennino ligure, toscano, romagnolo e sui rilievi della Sardegna, con apporti al suolo da deboli a moderati; al di sopra dei 1400-1700 m sull'Appennino centrale, con apporti al suolo deboli.

**Visibilità:** nessun fenomeno significativo.

**Temperature:** minime in generale e sensibile aumento al Centro e sul Nord-Est.

**Venti:** localmente forti sud-occidentali sulla Sardegna, con rinforzi di burrasca sui rilievi; localmente forti meridionali sulla Sicilia occidentale; localmente forti settentrionali sulla Liguria centrale; tendenti a forti dai quadranti meridionali sui settori ionici peninsulari, sulla Puglia e sul versante adriatico del Molise; forti sud-occidentali sui crinali dell'Appennino tosco-romagnolo e dell'Appennino centrale, campano e lucano.

**Mari:** molto mossi tutti i bacini occidentali e meridionali e l'Adriatico centrale al largo, fino ad agitati il Mare e il Canale di Sardegna.

## **FENOMENI SIGNIFICATIVI O AVVERSI PER IL GIORNO 25 GENNAIO 2026**

### **Precipitazioni:**

- da sparse a diffuse, anche a carattere di rovescio o temporale, su Liguria di Levante, Campania, settori tirrenici di Basilicata e Calabria settentrionale, Sicilia occidentale e coste della Sardegna nord-occidentale, con quantitativi cumulati generalmente moderati;

- da isolate a sparse sui restanti settori di Basilicata, Calabria tirrenica e Sardegna e su Valle d'Aosta, Piemonte centro-settentrionale, settori alpini, prealpini e di alta pianura della Lombardia, Triveneto, Toscana, Umbria, Marche meridionali, Lazio, Abruzzo, Molise, Puglia e Sicilia centrale e nord-orientale, con quantitativi cumulati generalmente deboli.

**Nevicate:** al di sopra dei 600-800 m sui settori alpini di Piemonte settentrionale e Lombardia, sulla Valle d'Aosta e settori occidentali del Trentino e dell'Alto Adige, con apporti al suolo da deboli a moderati; al di sopra degli 800-1100 m sui restanti settori alpini del Triveneto, con apporti al suolo da deboli a moderati; al di sopra dei 600-800 m sull'Appennino ligure e toscano, con apporti al suolo da deboli a moderati; al di sopra dei 1100-1300 m sull'Appennino laziale, abruzzese e molisano e dei 1200-1400 m sull'Appennino meridionale e sui rilievi delle due isole maggiori, con apporti al suolo deboli.

**Visibilità:** nessun fenomeno significativo.

**Temperature:** in generale calo le massime al Centro-Sud, anche sensibile sulle regioni meridionali.

**Venti:** forti sud-orientali sui settori ionici peninsulari e sulla Puglia centro-meridionale, con rinforzi di burrasca sulla Puglia meridionale; localmente forti sud-occidentali sulla Sardegna e sulle coste meridionali e arcipelago della Toscana.

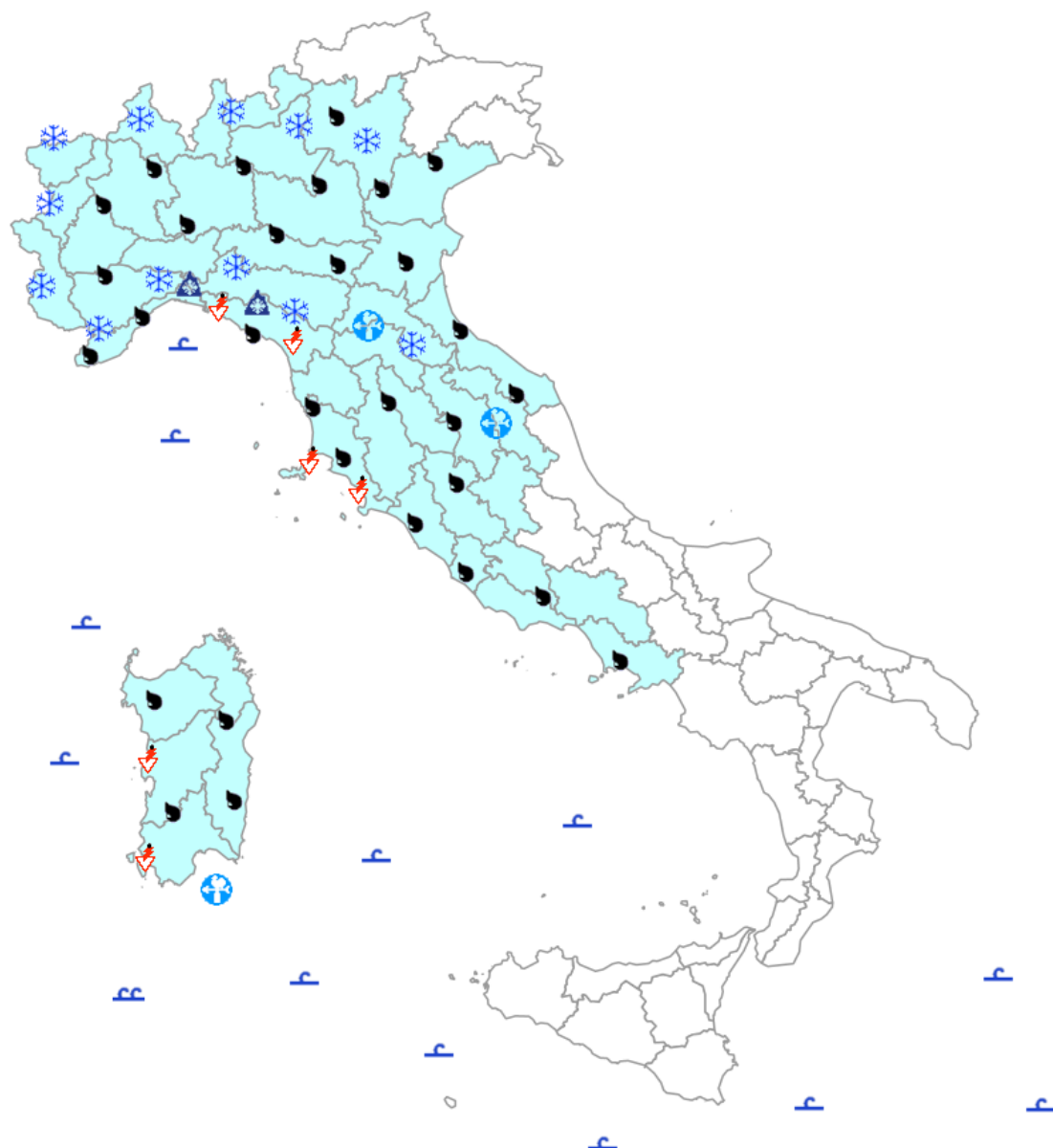
**Mari:** agitati l'Adriatico meridionale, lo Ionio centro-settentrionale, il Mare e il Canale di Sardegna e localmente lo Stretto di Sicilia; molto mossi i restanti bacini occidentali e meridionali e l'Adriatico centrale.

IL DIRIGENTE

## Fenomeni meteorologici significativi previsti per il giorno 23 GENNAIO 2026 (ORE 15-24)



### Centro Funzionale Centrale - Settore Meteo



#### LEGENDA

Aree di vigilanza meteo

#### Quantitativi giornalieri di Precipitazione previsti

Assenti o non rilevanti

Deboli

Moderati

Elevati

Molto elevati

#### Caratteristiche delle precipitazioni previste

Piogge sparse o intermittenti

Piogge diffuse e continue

Nevicate deboli o moderate

Nevicate abbondanti

Rovesci o temporali a carattere isolato

Rovesci o temporali a carattere sparso

Rovesci o temporali a carattere diffuso

#### Altri fenomeni meteorologici di rilievo

##### Venti

Forti

Burrasca

Tempesta

Frequenti raffiche

##### Mari

Molto mosso

Agitato o molto agitato

Grosso o molto grosso

##### Moto ondoso

In aumento

In diminuzione

##### Temperature

Elevate o in sensibile aumento

Molto elevate o in marcato aumento

Basse o in sensibile calo

Molto basse o in marcato calo

##### Gelate

Diffusa formazione di ghiaccio al suolo a quote collinari

Diffusa formazione di ghiaccio al suolo a quote di pianura

##### Nebbie

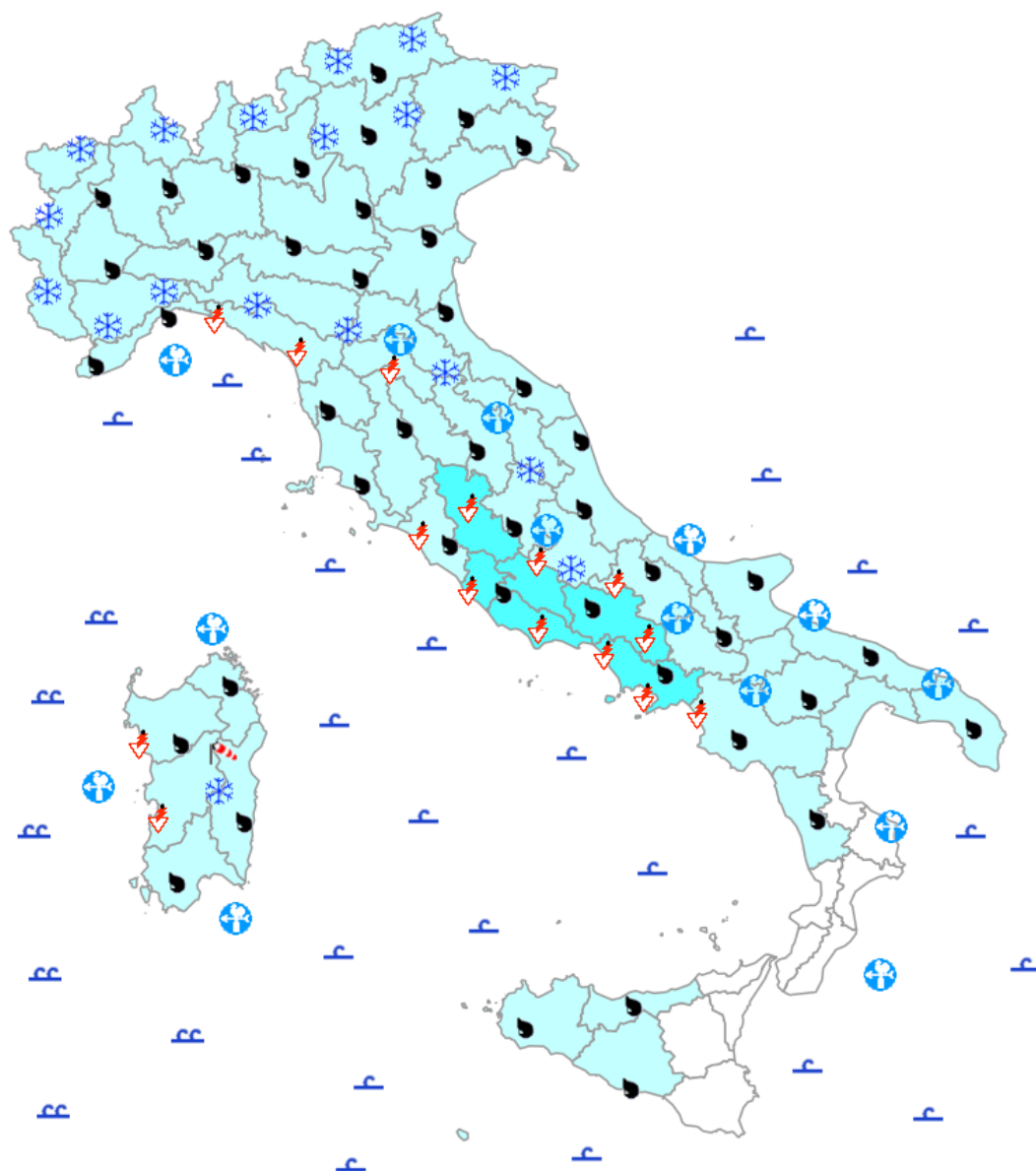
Nebbie diffuse nelle ore notturne e del primo mattino

Nebbie diffuse e persistenti anche nelle ore diurne

## Fenomeni meteorologici significativi previsti per il giorno 24 GENNAIO 2026



### Centro Funzionale Centrale - Settore Meteo



#### LEGENDA

Aree di vigilanza meteo

#### Quantitativi giornalieri di Precipitazione previsti

Assenti o non rilevanti

Deboli

Moderati

Elevati

Molto elevati

#### Caratteristiche delle precipitazioni previste

Piogge sparse o intermittenti

Piogge diffuse e continue

Nevicate deboli o moderate

Nevicate abbondanti

Rovesci o temporali a carattere isolato

Rovesci o temporali a carattere sparso

Rovesci o temporali a carattere diffuso

#### Altri fenomeni meteorologici di rilievo

##### Venti

Forti

Burrasca

Tempesta

Frequenti raffiche

##### Mari

Molto mosso

Agitato o molto agitato

Grosso o molto grosso

##### Moto ondoso

In aumento

In diminuzione

##### Temperature

Elevate o in sensibile aumento

Molto elevate o in marcato aumento

Basse o in sensibile calo

Molto basse o in marcato calo

##### Gelate

Diffusa formazione di ghiaccio al suolo a quote collinari

Diffusa formazione di ghiaccio al suolo a quote di pianura

##### Nebbie

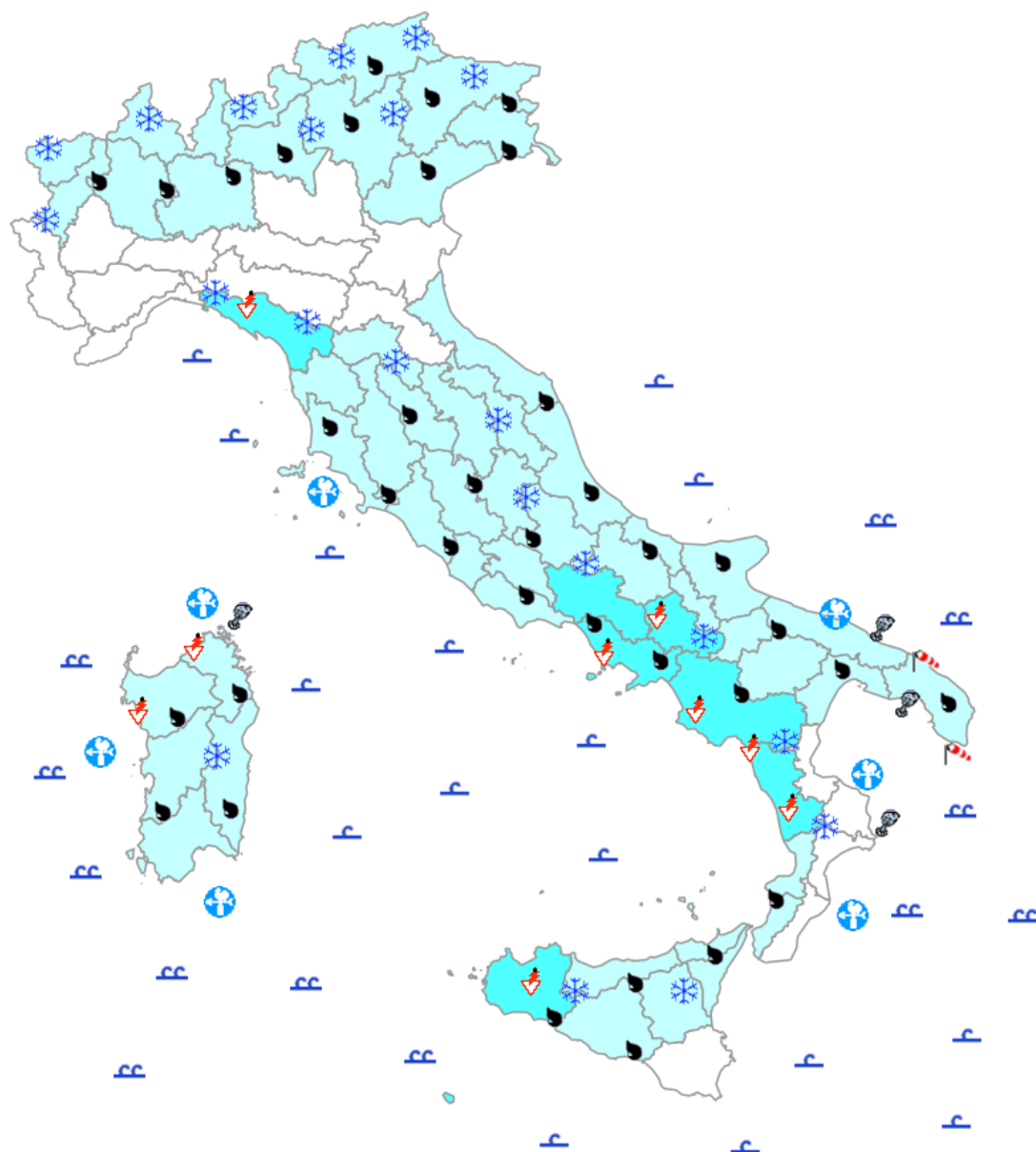
Nebbie diffuse nelle ore notturne e del primo mattino

Nebbie diffuse e persistenti anche nelle ore diurne

## Fenomeni metereologici significativi previsti per il giorno 25 GENNAIO 2026



### Centro Funzionale Centrale - Settore Meteo



#### LEGENDA

Aree di vigilanza meteo

#### Quantitativi giornalieri di Precipitazione previsti

Assenti o non rilevanti

Deboli

Moderati

Elevati

Molto elevati

#### Caratteristiche delle precipitazioni previste

Piogge sparse o intermittenti

Piogge diffuse e continue

Nevicate deboli o moderate

Nevicate abbondanti

Rovesci o temporali a carattere isolato

Rovesci o temporali a carattere sparso

Rovesci o temporali a carattere diffuso

#### Altri fenomeni meteorologici e rilievo

##### Venti

Forti

Burrasca

Tempesta

Frequenti raffiche

##### Mari

Molto mosso

Agitato o molto agitato

Grosso o molto grosso

##### Moto ondoso

In aumento

In diminuzione

##### Temperature

Elevate o in sensibile aumento

Molto elevate o in marcato aumento

Basse o in sensibile calo

Molto basse o in marcato calo

##### Gelate

Diffusa formazione di ghiaccio al suolo a quote collinari

Diffusa formazione di ghiaccio al suolo a quote di pianura

##### Nebbie

Nebbie diffuse nelle ore notturne e del primo mattino

Nebbie diffuse e persistenti anche nelle ore diurne